Precio de las viviendas en Medellín según su Ubicación

Propuesta de proyecto para el curso de Análisis Geoespacial

Kevin Parra
Universidad Nacional de Colombia
keparrah@unal.edu.co

Made with GAMMA

Descripción del Problema de Investigación

El precio de una vivienda no depende únicamente de sus características internas, como el área, el número de habitaciones o el número de baños. En Medellín, la ubicación también puede influir significativamente en el precio, ya que cada barrio cuenta con su propia oferta comercial, de transporte, de servicios y un entorno particular que lo caracteriza.

Este proyecto busca estudiar cómo se relaciona la ubicación geográfica de una vivienda en Medellín con su precio, explorando patrones espaciales y factores que determinan las diferencias de valor.

Pregunta de Investigación

¿Cómo se relaciona la ubicación geográfica de una vivienda en Medellín con su precio?

Made with GAMMA

Base de Datos

Colombia House Pricing Dataset

La fuente principal será el dataset disponible en Kaggle, que contiene registros de viviendas en Colombia y será filtrado para trabajar únicamente con Medellín.

Aunque tiene aproximadamente 3 años de antigüedad, se usará con fines académicos, por lo cual la desactualización no representa una limitación crítica para esta primera aproximación.

Ver dataset en Kaggle

Made with GAMMA

Variables y Características del Dataset

Ubicación

Latitud y longitud para georreferenciar cada vivienda

Precio

De venta para cada propiedad

Área total

Metros cuadrados construidos

Habitaciones

Número de habitaciones en la vivienda

Baños

Número de baños completos

Tipo de vivienda

Categorización del inmueble

1M

Registros totales

En el dataset nacional de Colombia

260K

Viviendas en Medellín

Registros identificados para la ciudad

Made with GAMMA

id	lat	lon	l3	rooms	bathrooms	price	property_type
1000000 unique values	-75.6 … 85.1	-180 … 100	Medellín 26% Bogotá D.C 17% Other (565976) 57%	1 … 40	1 … 20	0 … 1600b	Apartamento 57% Casa 22% Other (214495) 21%
KsjahK62rxcYKXXQjOdkqw==	3.921	-76.506			7	1300000000	Casa
Y+gsBZYq1zu5NoR3V5oUGA==	3.3577005	-76.5418112	Cali		7	2800000000	Casa
Jpzqxj8/Vgf3Aa5ASxUBNg==	3.3577005	-76.5418112	Cali		7	2800000000	Casa
ieuFnkFx/yHDD66iMV14Gw==	3.364	-76.538	Cali		8	3500000000	Casa
g4u5JM+hAHEk8SukRSjMzg==	3.391	-76.517	Cali		9	480000000	Casa
+S9T8NKJ/yyndMxxRz1emQ==	3.413	-76.544	Cali		10	1400000000	Casa
0DBic9QJv2FL9Oq0S+xaSA==	3.451	-76.532	Cali		7	280000000	Casa
0/S4PBWArkYd3NDMyZZtPQ==	3.427	-76.542	Cali		7	530000000	Casa
mrYI162HS5qJaAFN2WpP2Q==	3.364	-76.538	Cali		9	7000000	Casa
3q8MmfVZHtWJa6pxNnypeg==	3.565	-76.551	Cali		7	1700000000	Casa

Made with GAMMA

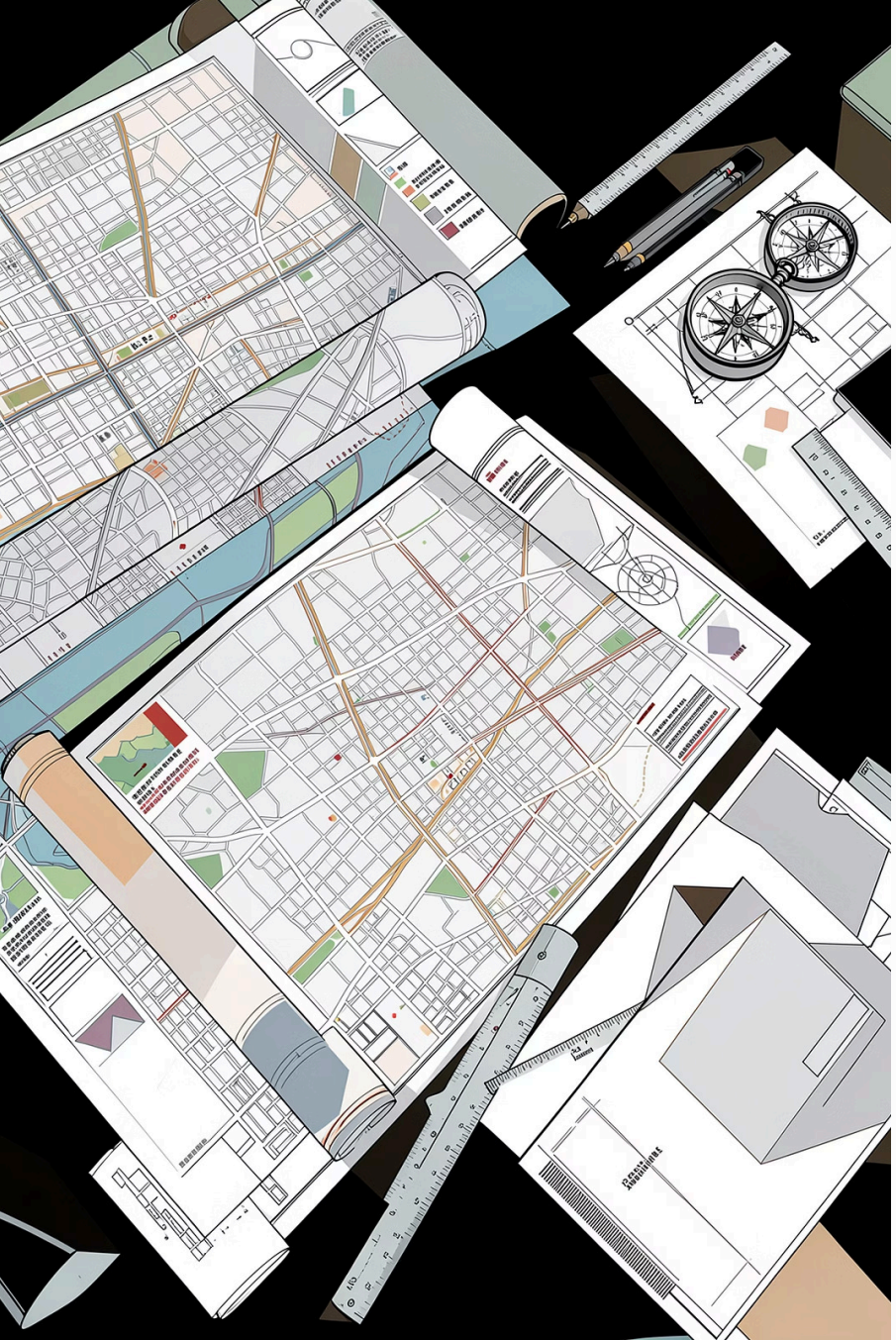

Fuentes Complementarias e ideas de aplicación

Además del dataset principal, se podrían revisar fuentes públicas de Medellín para enriquecer el análisis y proporcionar contexto territorial.

OIME - Observatorio Inmobiliario de Medellín

Información oficial sobre el mercado inmobiliario de la ciudad

Visitar OIME

Portal Geográfico Metropolitano

Datos geográficos y territoriales de la región metropolitana

Visitar Portal Geográfico

Made with GAMMA

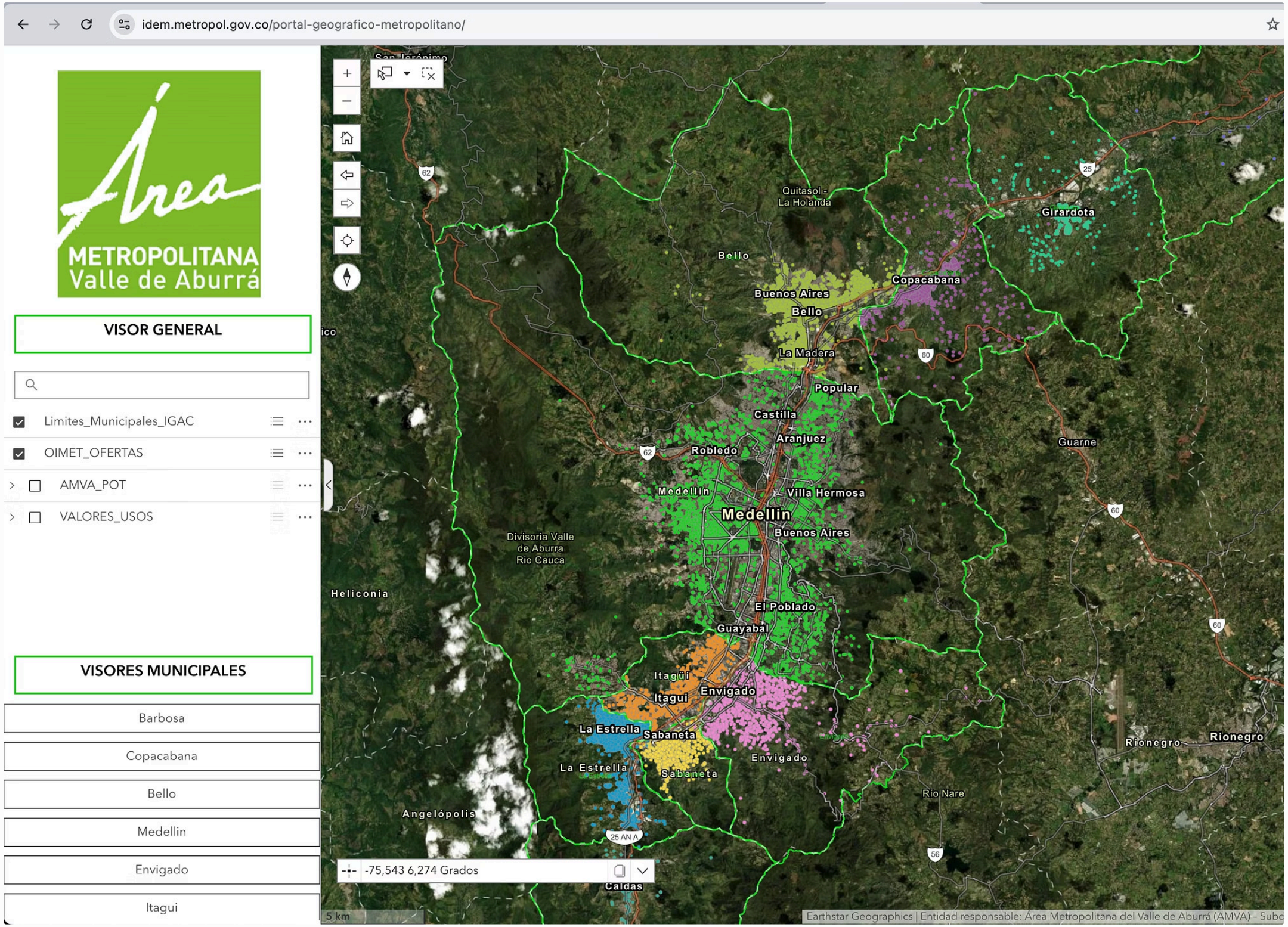

Portal geográfico metropolitano

Made with GAMMA

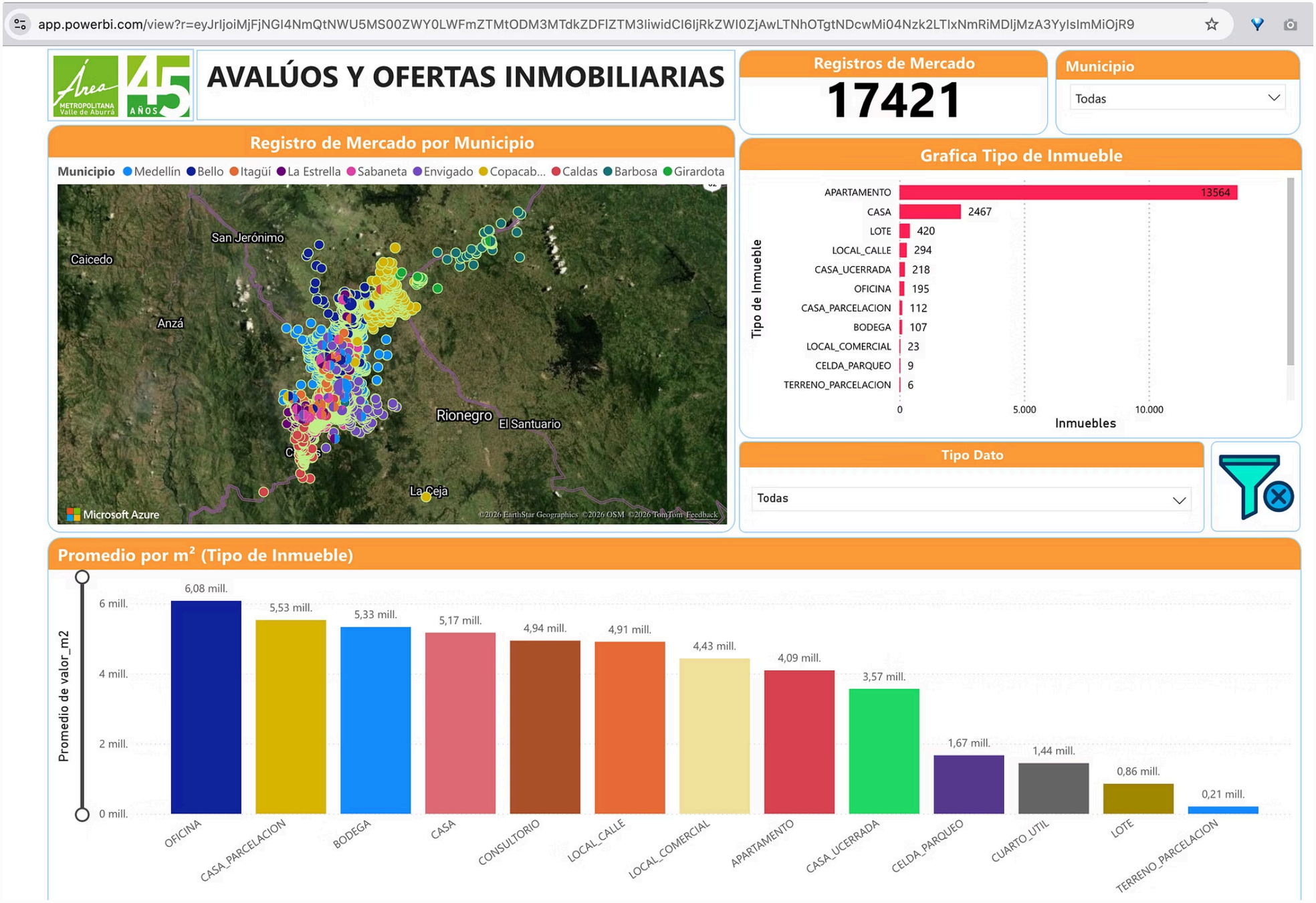

Observatorio Inmobiliario de Medellín

Made with GAMMA